Manuel utilisateur du plugin « Assistant DFCI »
V1.0.0

Identifiant			Version	Date de création
			1.0.0	24/07/2025
Rédacteur	Gérôme PECHEUR			
Entité émettrice	DTSO			
Diffusion	☐ Interne	■ Ouverte	☐ Limitée	
Résumé	Installation et utilisation du plugin			
Approbateur		Date d'approbation	10/01/2025	

Lecteur(s)	

Version	Date	Modifié par	Historique des modifications
0.1	10/01/2025	Gérôme PECHEUR	Création
1.0.0	08/07/2025	Gérôme PECHEUR	Adaptation à le version 1.0.0 du plugin

Sommaire

1 PREREQUIS 2
2 RESUME 3
3 INSTALLATION 3
4 PRESENTATION 4
5 MODE DE SELECTION 5
5.1 Sélection unique 5
5.2 Sélection multiple 5
6 MODIFICATION 5
7 EXTRA 6
7.1 A propos de 6

1 Prérequis

Version de QGIS : 3.28 ou supérieur

Ce plugin fonctionne en parallèle du plugin « IGN Espace collaboratif » version 4.2.2

Ce plugin fonctionne uniquement avec des couches de la BDTopo, le nom de la couche route doit obligatoirement se nommer : « troncon_de_route » dans QGIS.

Si le package « openpyxl » n'est pas installé sur le poste le message d'erreur ci-dessous apparait lors d'une transaction.

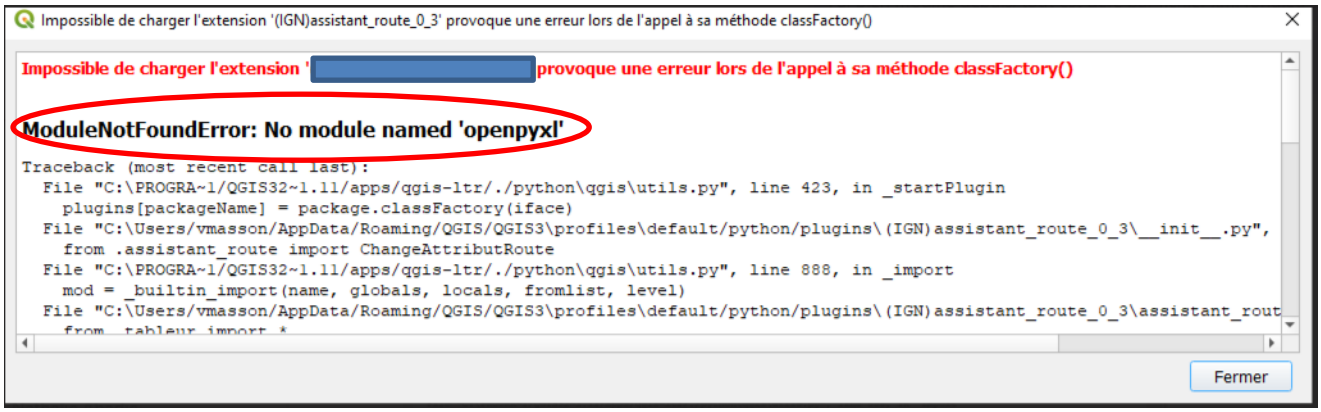

Remède : installation du package.

Ouvrir l'invite de commande, se placer dans le répertoire « bin » de l'installation de QGIS :

Exemple :

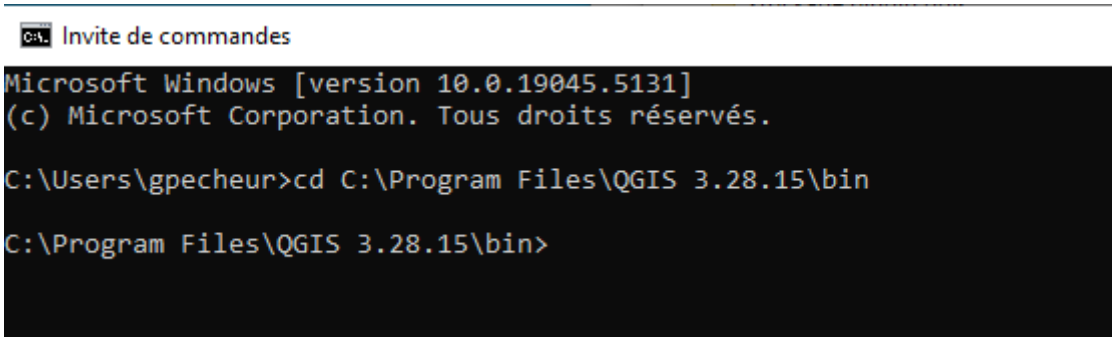

Puis taper la commande : python-qgis-ltr.bat -m pip install openpyxl

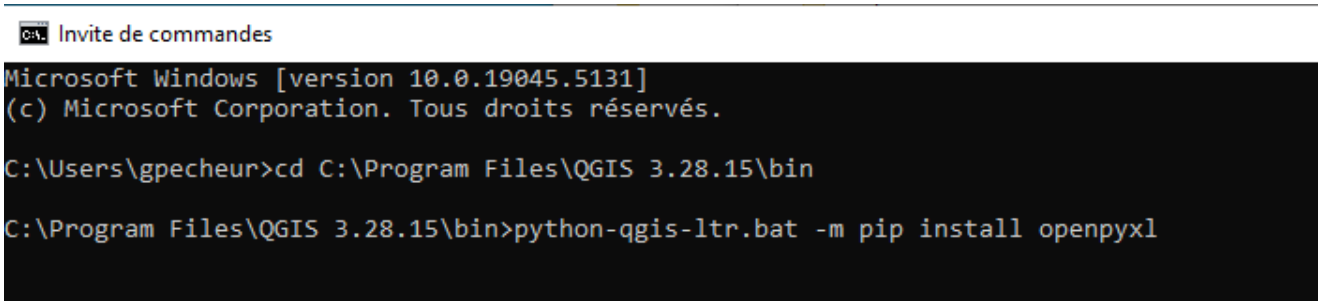

Le package s'installe, vous n'avez plus qu'à relancer QGIS.

2 Résumé

Ce plugin est une aide à la modification des attributs sémantiques des complexes DFCI

3 Installation

Ouvrir QGIS.

Allez dans Extensions/Installer/Gérer les extensions, cliquez sur Installer depuis un ZIP, sélectionner le fichier ZIP puis cliquez sur Installer le plugin.

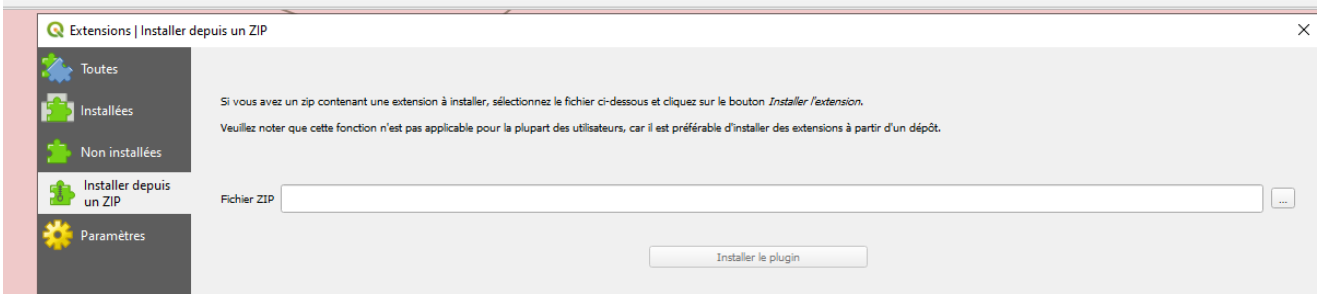

4 Présentation

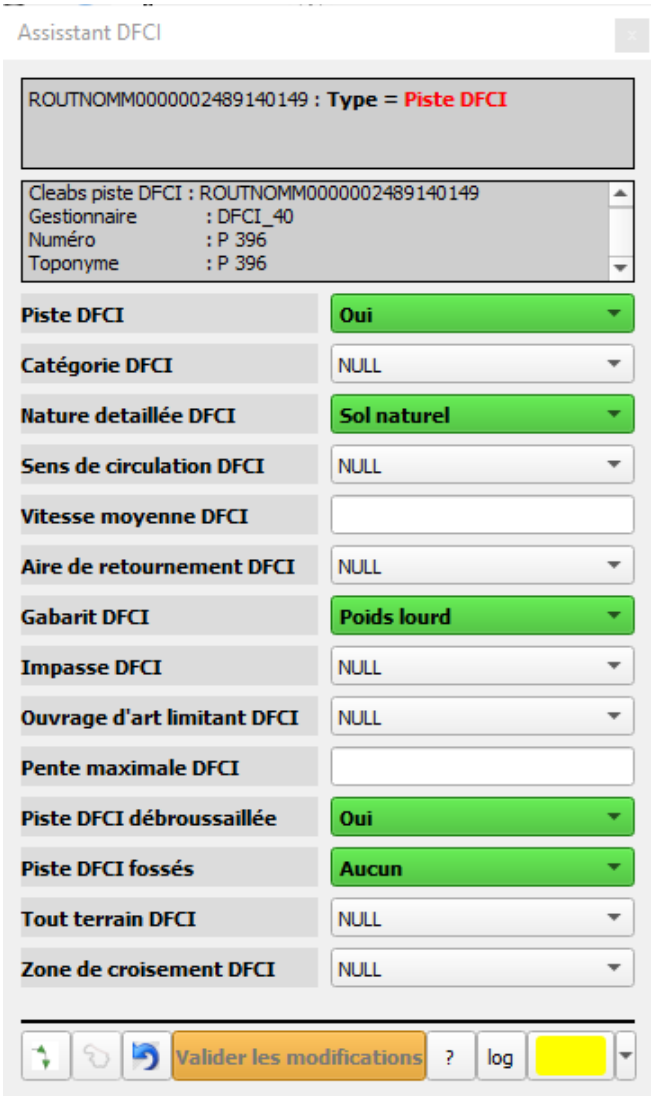

Cette interface permet de modifier les attributs des champs DFCI des tronçons de routes

Le bouton « ? » permet d'afficher le suivi des versions et permet également d'ouvrir la documentation du plugin
Le bouton « log » permet d'afficher le rapport des modifications

Le bouton permet d'annuler la dernière modification effective et uniquement la dernière.

Le bouton 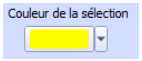

Permet de modifier la couleur des tronçons sélectionnés dans QGIS. Ça peut être utile suivant la symbologie appliquées pour les tronçons dans QGIS.

Le bouton permet la sélection de toutes les entités comprises entre deux tronçons.

Le bouton « Valider les modifications> valide les modifications dans QGIS, le plugin « espace collaboratif » se charge d'impacter les bases BDTopo de l'ign.

5 Mode de sélection

5.1 Sélection unique

Les attributs affichés sont ceux du tronçon sélectionné ;
En vert lorsqu'ils sont différents de « NULL » ou de vide.

5.2 Sélection multiple

- Sélection multiple avec l'outil de saisi. Dans QGIS on peut sélectionner manuellement un ensemble de tronçons
- Sélection multiple de tronçons contigües, on sélectionne 2 tronçons, Ces 2 tronçons doivent être visible à l'écran et être connectés. Ensuite en clique sur , le résultat est une sélection de tous les tronçons entre le premier et le deuxième sélectionné respectant l'algorithme du chemin le plus court. Un contrôle visuel est toutefois nécessaire afin de vérifier si les tronçons sont bien ceux désirés.

  Seuls les attributs communs à tous les tronçons sont représentés en vert.

6 Modification

Une fois les tronçons sélectionnés il suffit de choisir le ou les attributs à modifier.

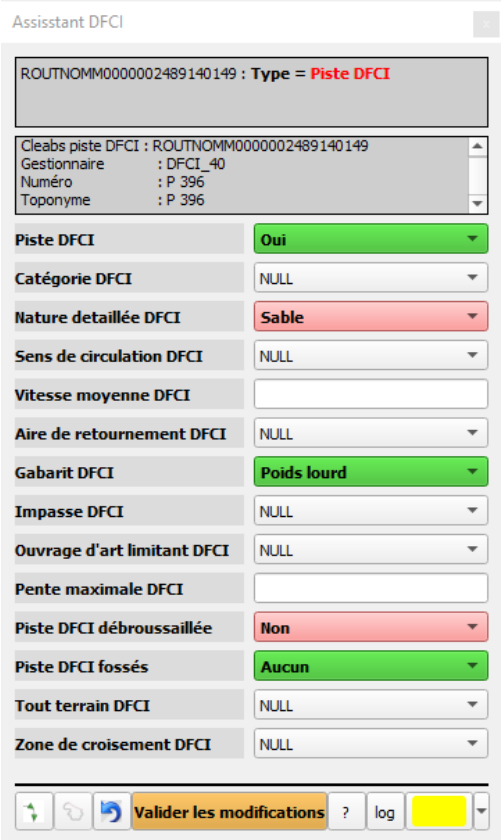

Les attributs en rose seront ceux qui seront modifiés pour tous les tronçons sélectionnés.

Les modifications sur le(s) tronçon(s) sélectionné(s) sont à valider avec le bouton

Un message QGIS confirme la prise en compte des modifications.

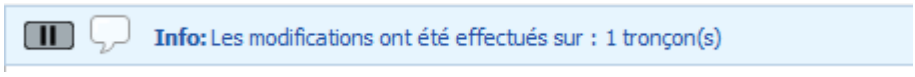

Attention : seule la base client est modifiée. Pour envoyer les modifications sur le serveur BDUni il faut le faire par l'intermédiaire du plugin espace collaboratif IGN, en cliquant sur l'enregistrement de la couche (disquette):

7 Extra

7.1 A propos de

Accessible via

.

Cette boite permet de suivre l'historique des différentes versions ainsi que d'afficher la documentation.